Anlage 4

Luftbild

A 4

© Bayerische Vermessungsverwaltung 2024, EuroGeographics

Michael Bär - Dipl. Ing. des Bauwesens (FH)
83224 Grassau – Ortenburger Str. 29a – Tel.: 08641 / 69 51 93 – Fax: 08641 / 69 51 96
Von der Industrie- und Handelskammer öffentlich bestellter und vereidigter Sachverständiger für die Bewertung von bebauten und unbebauten Grundstücken einschl. Mieten und Pachten. Zuständig: IHK Nürnberg.

Anlage 5
Pläne
BK A
A5.1

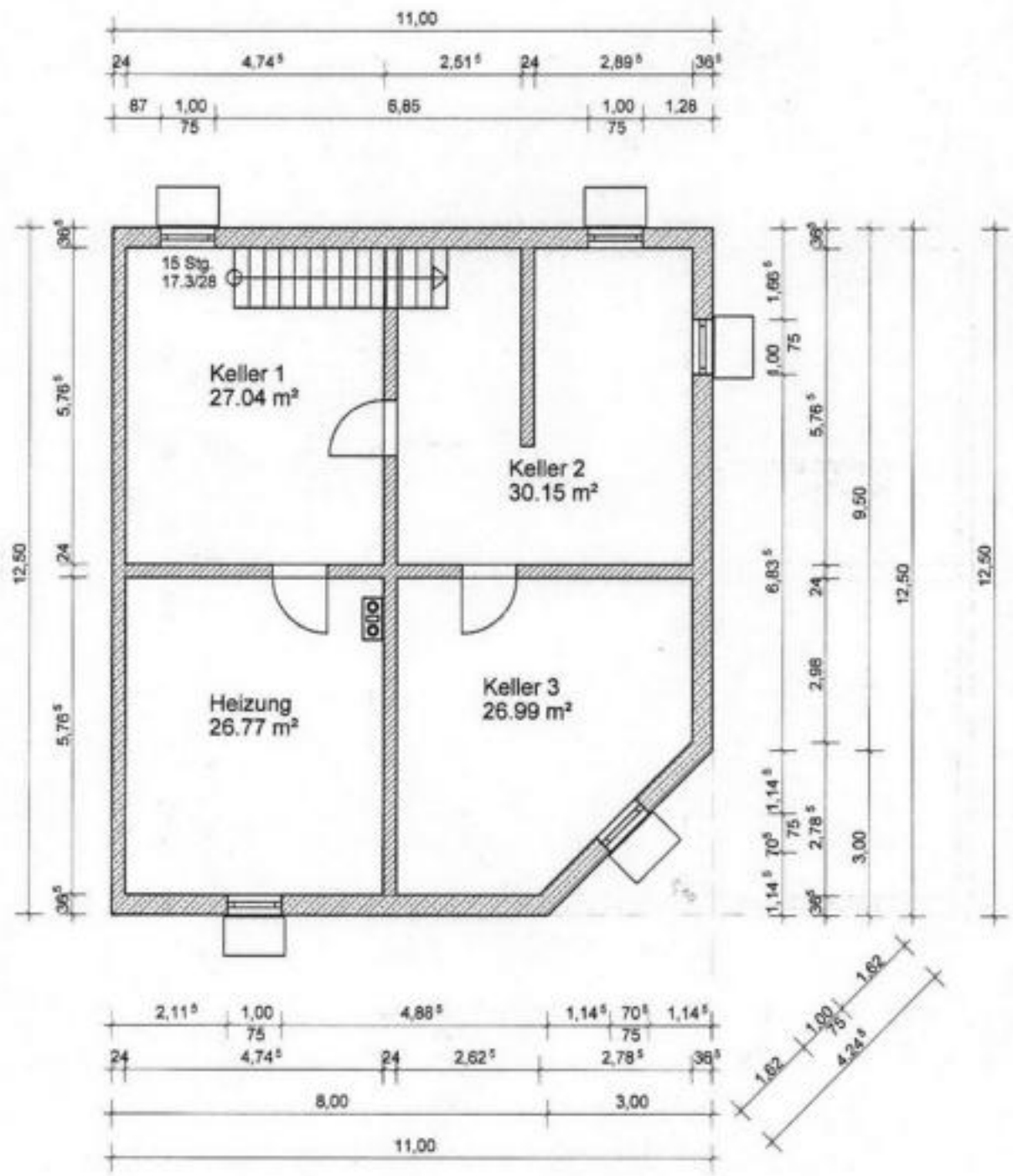

Keller

-Abweichungen sind vorhanden-

Anlage 5
Pläne
BK A
A5.2

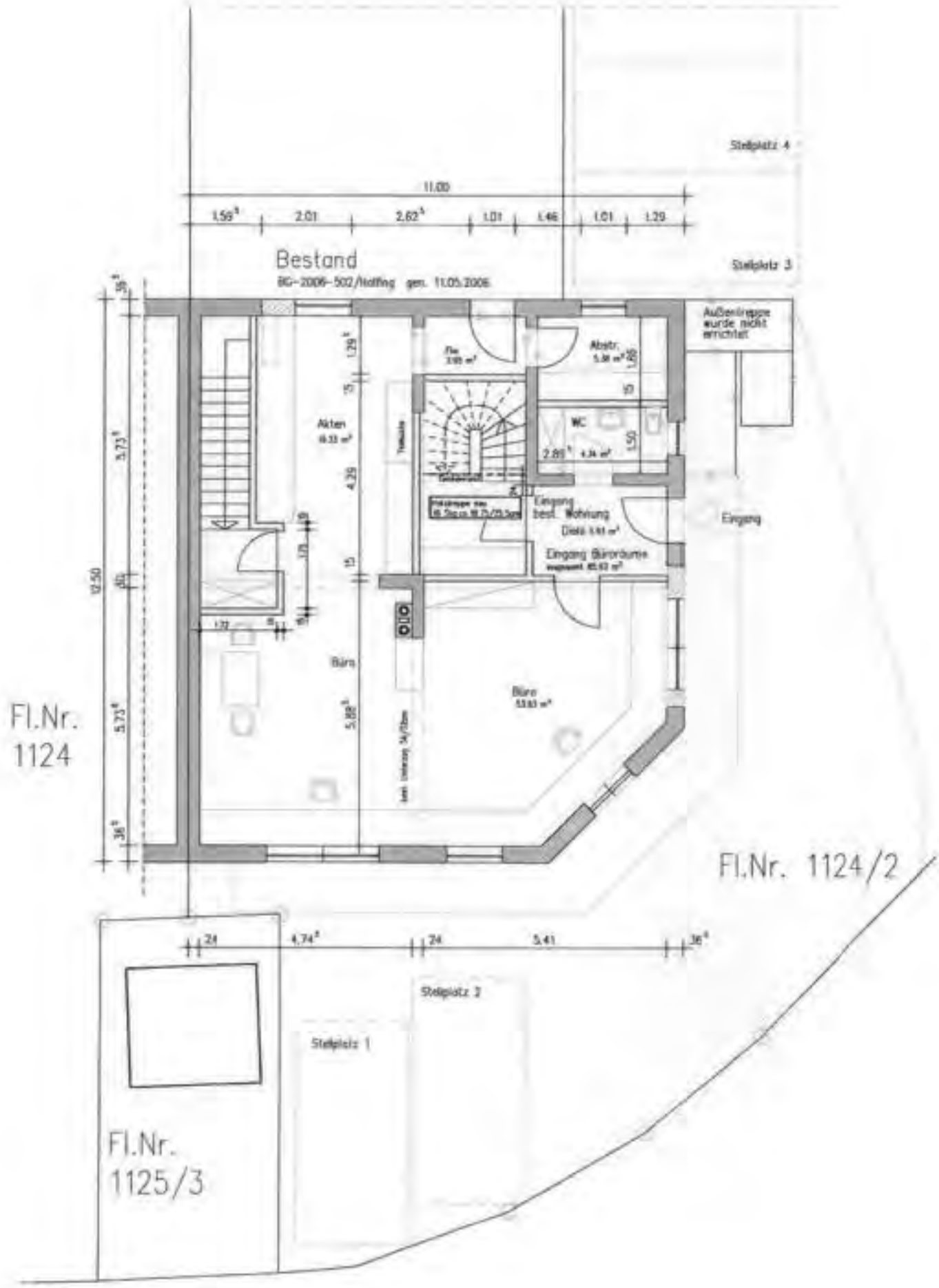

Erdgeschoss

-Abweichungen sind vorhanden-

Anlage 5
Pläne
BK A
A5.3

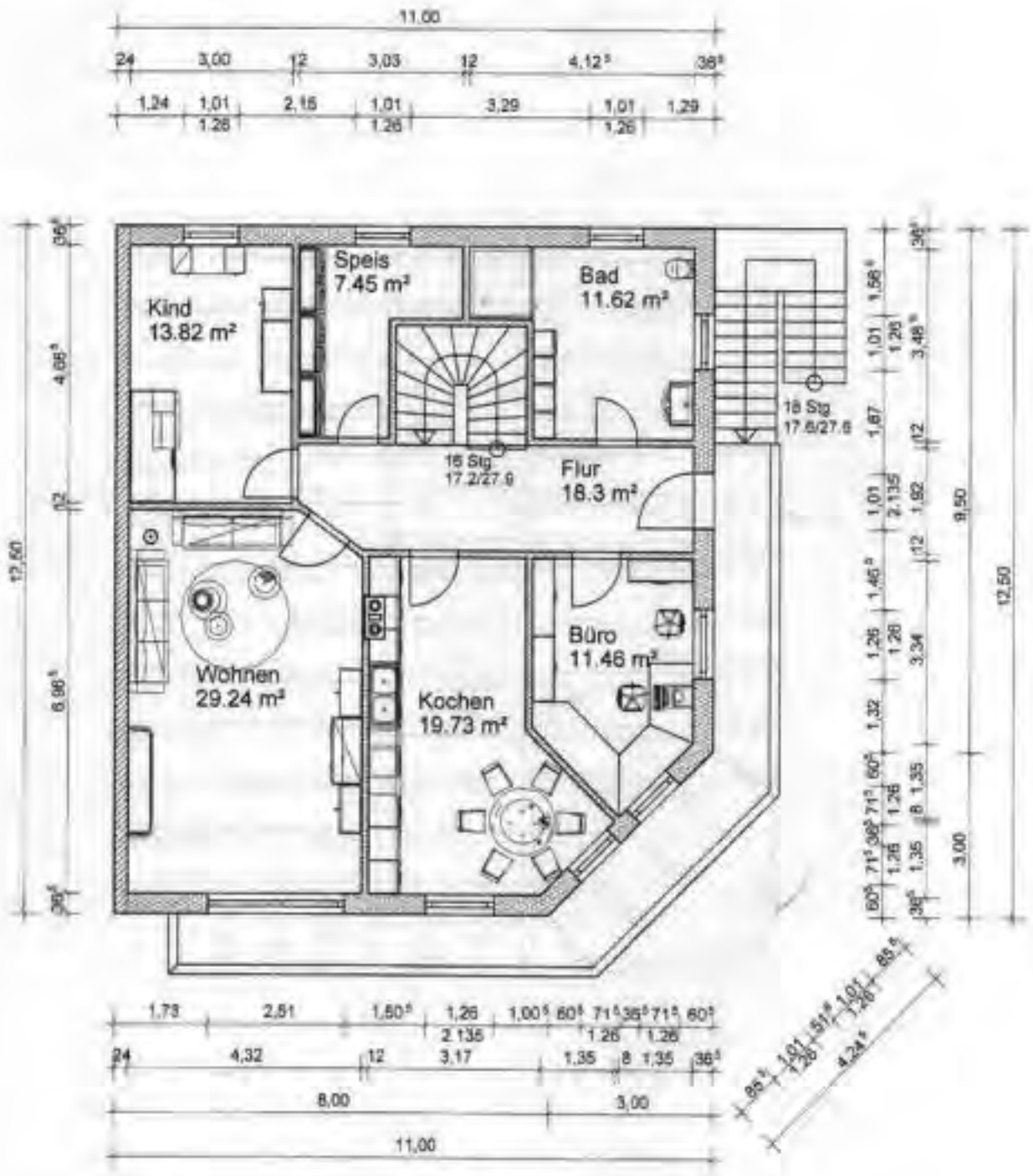

Obergeschoß

-Abweichungen sind vorhanden-

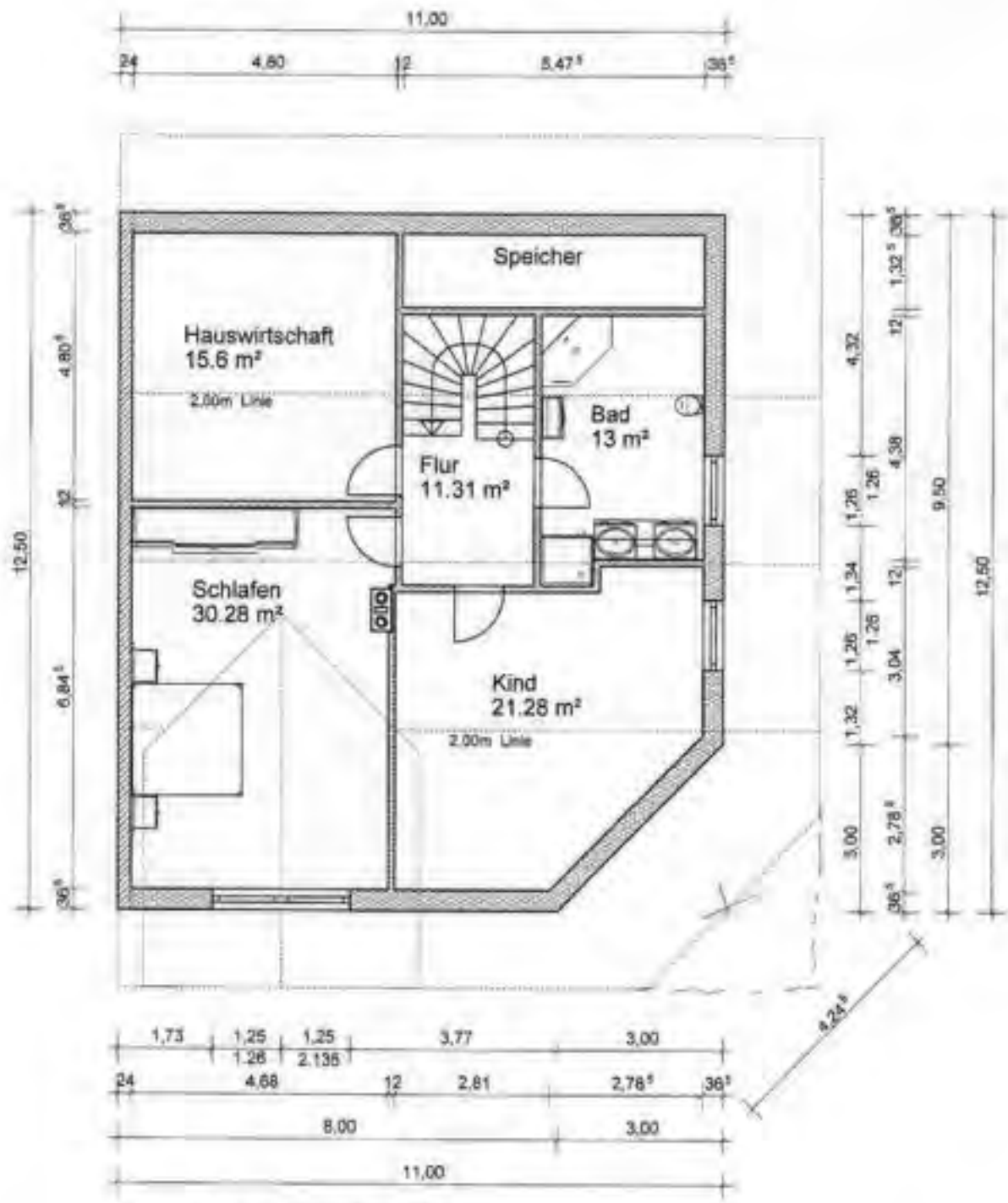

Dachgeschoß

-Abweichungen sind vorhanden-

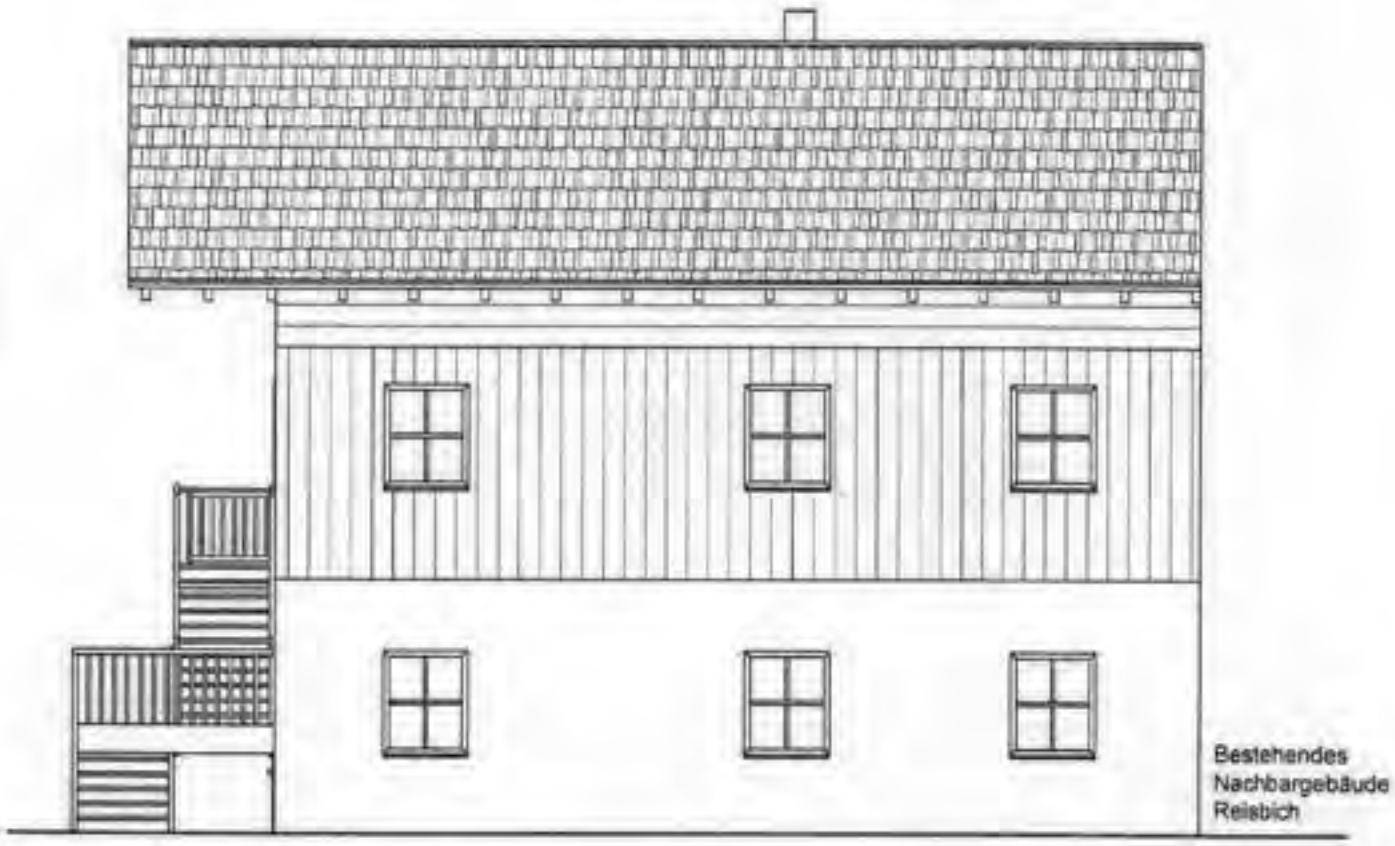

Norden

-Abweichungen sind vorhanden-

Ansicht von Osten

-Abweichungen sind vorhanden-

Süden

-Abweichungen sind vorhanden-

Anlage 5
Pläne
BK A
A5.8

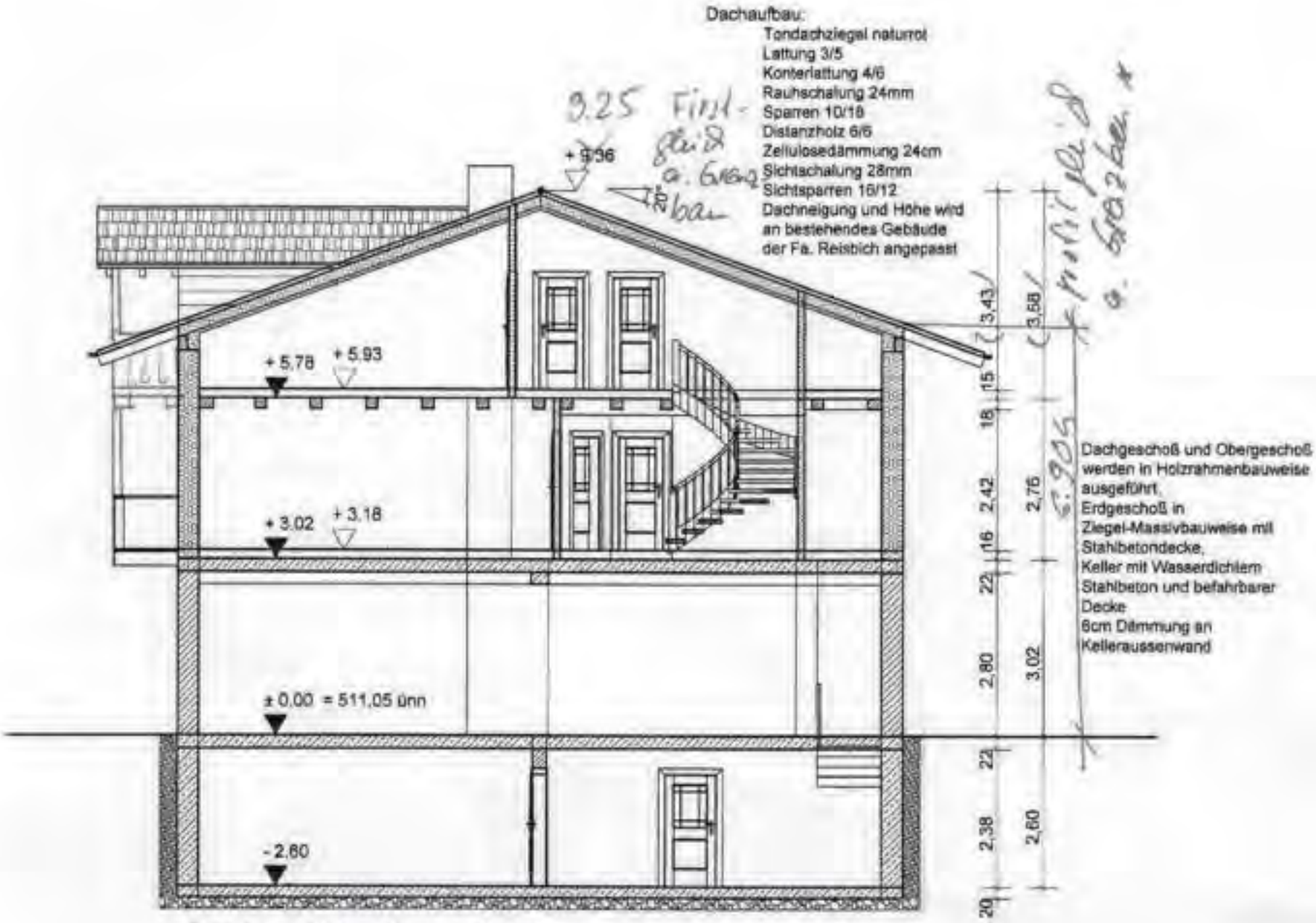

Schnitt A - A

-Abweichungen sind vorhanden-

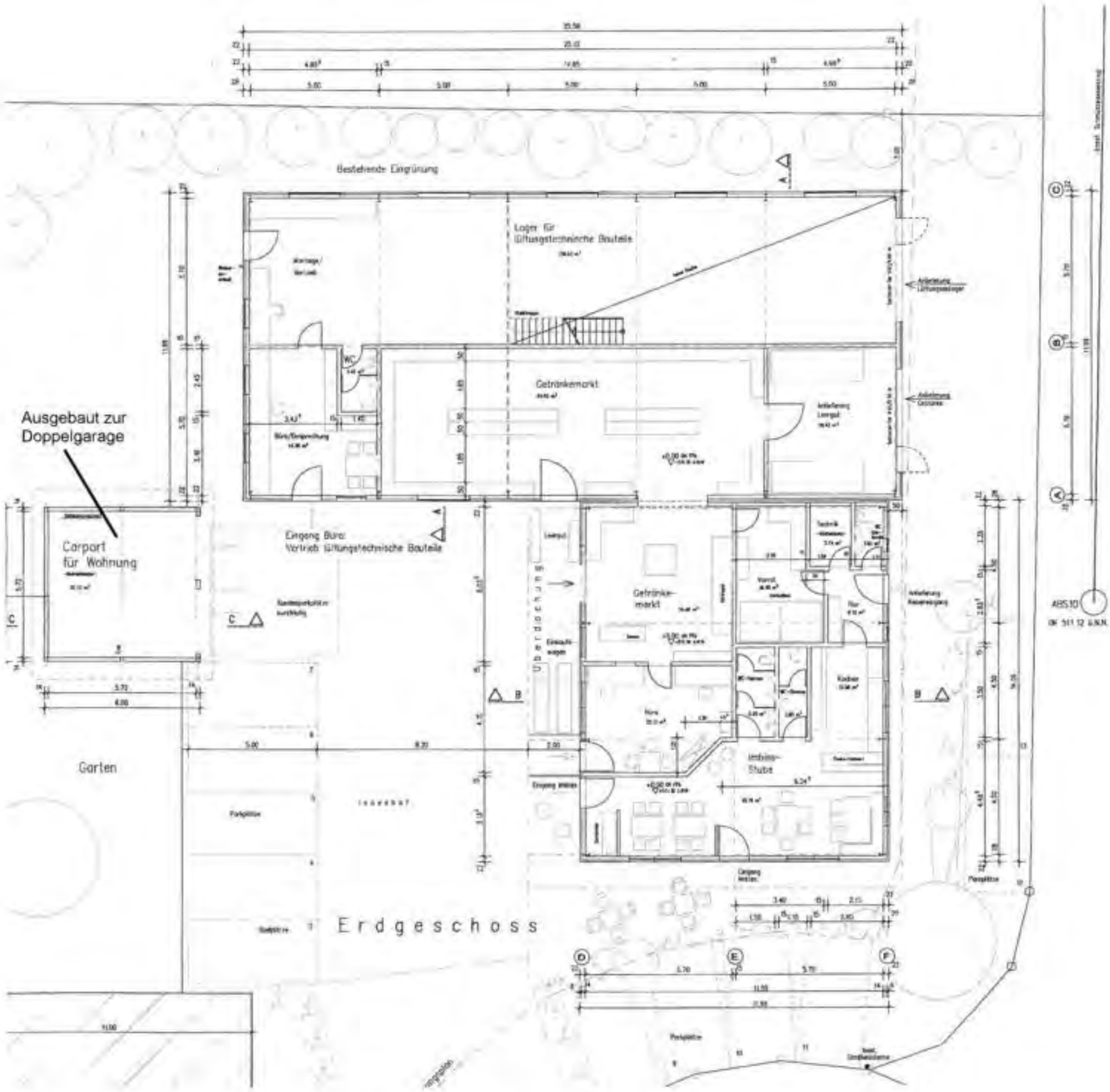

-Abweichungen sind vorhanden-

Anlage 6
Plane
BK B
A6.1

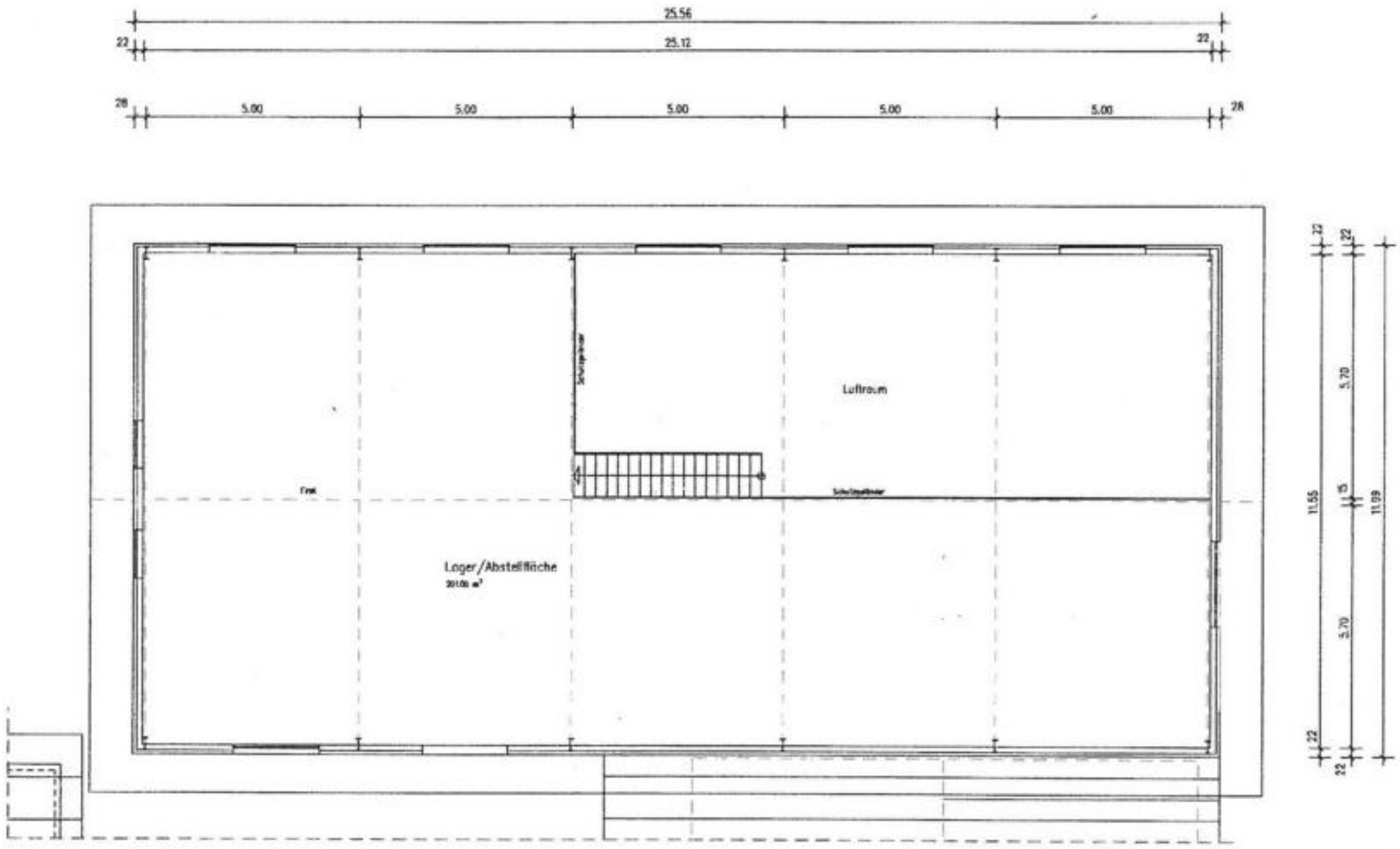

Obergeschoss

-Abweichungen sind vorhanden-

Anlage 6
Pläne
BK B
A6.2

Ansicht von Norden

-Abweichungen sind vorhanden-

Anlage 6
Pläne
BK B
A6.3

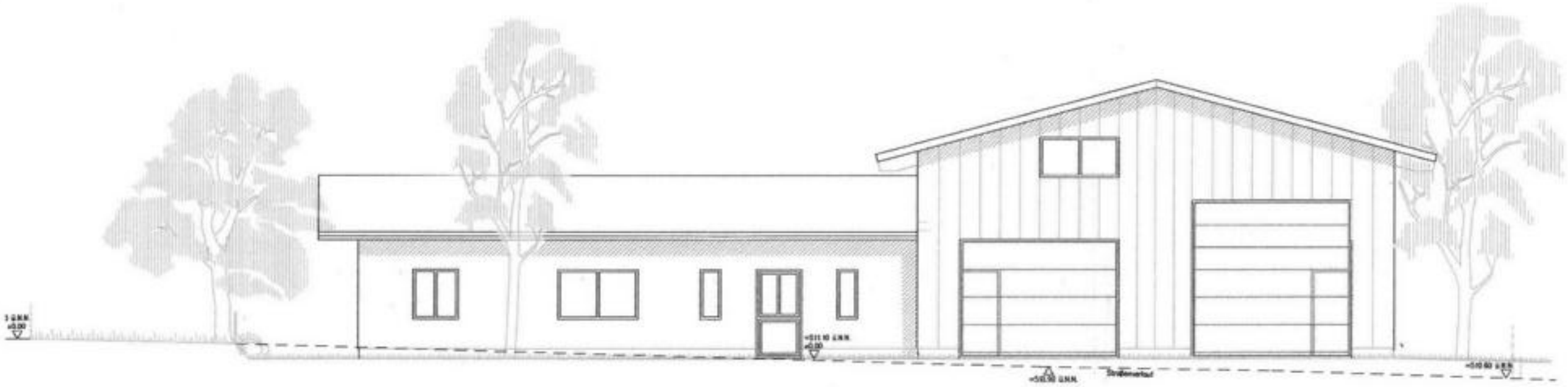

Ansicht von Osten

-Abweichungen sind vorhanden-

Anlage 6
Pläne
BK B
A6.4

Ansicht von Westen

-Abweichungen sind vorhanden-

Anlage 6
Pläne
BK B
A6.5

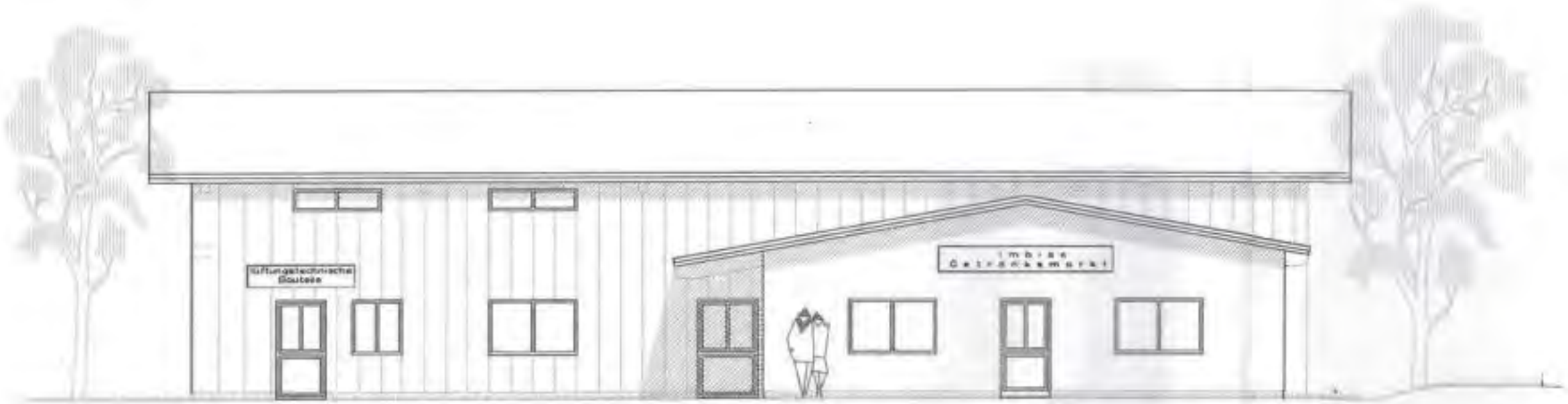

Ansicht von Süden

-Abweichungen sind vorhanden-

Anlage 6
Pläne
BK B
A6.6



Ansicht von Westen

Ansicht von Süden bzw. Norden



Ansicht von Osten

Ansichten Garage

EINGABEPLAN

-Abweichungen sind vorhanden-

Anlage 6
Pläne
BK B
A6.7

Anlage 6
Pläne
BK B
A6.8

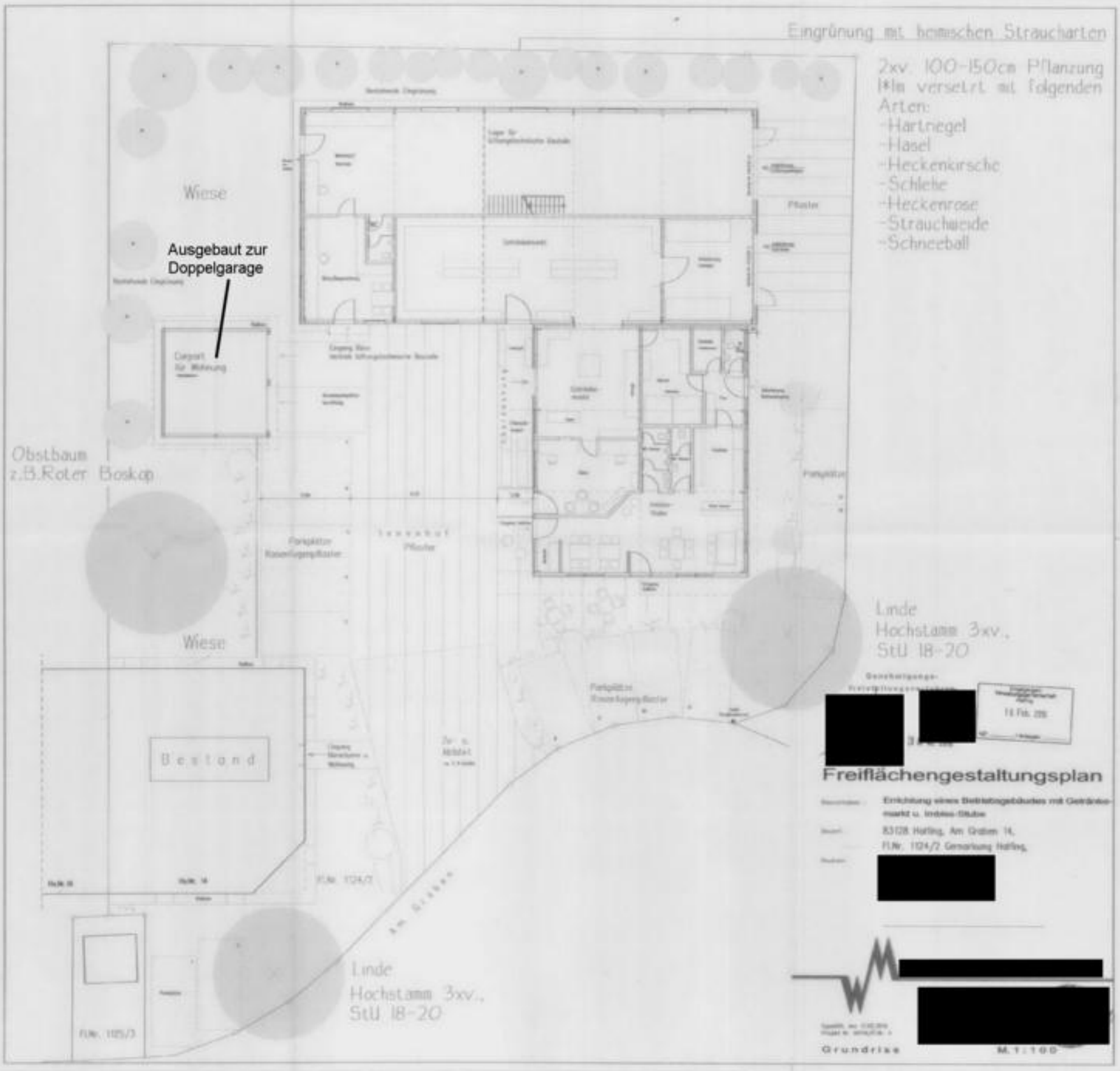

-Abweichungen sind vorhanden-

Anlage 7

Wohn-/Nutzfläche

A 7.1

Wohn-/Nutzfläche

Anmerkung:
Die angegebenen Flächen genügen in ihrer Genauigkeit dem Gutachten. Für eine weitere Verwendung für andere Zwecke sind diese Angaben nicht geeignet bzw. es wird keine Gewähr für derartige Verwendungen übernommen

BK A:

Nutzfläche EG

					m²
Büro					53,93
Akten					19,33
Flur					2,95
AR					5,38
WC					4,34
Zwischensumme					85,93
abzgl. 3% Putz					-2,58
Nutzfläche EG				**ca.**	**83**

Wohnfläche OG

	m	m	Faktor	m²	m²
Wohnen					29,24
Kochen					19,73
Büro					11,46
Bad					11,62
Speise					7,45
Kind					13,82
Flur					18,30
Zwischensumme					111,62
abzgl. 3% Putz					-3,35
zzgl. Balkon zu 1/4	5,00	1,20	0,25	1,50	
	7,25	0,90	0,25	1,63	
	5,95	1,00	0,25	1,49	4,62
Wohnfläche OG				**ca.**	**113**

Wohnfläche DG

					m²
Schlafen					30,28
Kind					21,28
Bad					13,00
HWR					15,60
Flur					11,31
Zwischensumme					91,47
abzgl. 3% Putz					-2,74
zzgl. Balkon				rd.	0,70
Wohnfläche DG				**ca.**	**89**
Wohnfläche OG u. DG				**ca.**	**202**

Anlage 7

Wohn-/Nutzfläche

A 7.2

BK B:

Nutzfläche EG

gem. Nutzflächenberechnung

		m²
Lager f. lüftungstechn. Bauteile		166,45
Getränkemarkt		169,60
Imbiss-Stube		93,71
Nutzfläche EG	**ca.**	**430**

Nutzfläche OG

gem. Nutzflächenberechnung

		m²
Lager/Abstellraum		201,00
Nutzfläche OG	**ca.**	**201**
Nutzfläche BK B, gesamt	**ca.**	**631**

(gemäß genehmigtem Bauplan)

Bauvorhaben: Errichtung eines Betriebsgebäudes mit Getränkemarkt u. Imbiss-Stube
Bauort: 83128 Halfing, Am Graben 14, Fl.Nr. 1124/2 der Gemarkung Halfing
Bauherr: [redacted]

Nutzfläche

<u>Lager für lüftungstechische Bauteile:</u>			
Erdgeschoss:			
Lager	25,12*5,70 - 4,42*1,03	138,63 m²	
Büro/Besprechung	5,70*4,985 - 1,55*2,60	24,38 m²	
WC	2,45*1,40	3,43 m²	
		166,45 m²	
Obergeschoss:			
Lager/Abstellraum	11.55*10.00 + 5.70*15.00	201,00 m²	
			367,45 m²
<u>Getränkemarkt:</u>			
Getränkemarkt	6,035*5,70 + 14,85*5,70	119,04 m²	
Leergut/Anlieferung	4,985*5,70	28,41 m²	
Büro	5,70*4,15 - 0,45*1,35 - 1,35*1,35/2	22,14 m²	
			169,60 m²
<u>Imbiss-Stube:</u>			
Imbiss-Stube:	11,55*3,135 +3,76*1,35 +1,35*1,35/2	42,20 m²	
WC-Herren	1,50*3,50	5,25 m²	
WC-Damen	1,10*3,50	3,85 m²	
Kochen	4,85*2,80	13,58 m²	
Vorrat/Kühlzellen	3,40*2,835+2,70*2,50	16,39 m²	
Flur	2,15*2,835	6,10 m²	
WC/Umkleide	2,35*1,11	2,61 m²	
Technik	2,35*1,59	3,74 m²	
			93,71 m²
Nutzfläche gesamt:			**630,75 m²**

Amtsgericht Rosenheim

Grundbuch

von

Halfing

Blatt 2490

Amtsgericht Rosenheim
Grundbuch von Halfing **Blatt** 2490 **Bestandsverzeichnis** Einlegebogen 1

Lfd. Nr. der Grundstücke	Bisherige lfd. Nr. d. Grundstücke	Bezeichnung der Grundstücke und der mit dem Eigentum verbundenen Rechte: Gemarkung Flurstück a/b	Wirtschaftsart und Lage c	Größe ha	a	m²
1	2	3		4		
1	-	1124/2	Nähe Am Graben, Bauplatz		19	02
2	1	1124/2	Nähe Am Graben, Gebäude- und Freifläche		18	06
	1	[redacted]				96
3	2	1124/2	Am Graben 14, Gebäude- und Freifläche		18	06

Anlage 8
Grundbuchauszug
A8.1

Amtsgericht Rosenheim
Grundbuch von Halfing **Blatt** 2490 **Bestandsverzeichnis** Einlegebogen 1 R

Bestand und Zuschreibungen		Abschreibungen	
Zur lfd. Nr. der Grundstücke		Zur lfd. Nr. der Grundstücke	
5	6	7	8
1	Lt. VN. 1046 von Bl. 1942 übertragen am 03.12.1998 [redacted]	2	FN 1205: Flst. 1124/3 übertragen nach Blatt 1999; eingetragen am 08.12.2006. [redacted]
1,2	FN 1200: BVNr. 1 nach Zerlegung als ein Grundstück unter BVNr. 2 neu vorgetragen am 04.09.2006. [redacted]		
2,3	FN 1218: BV-Nr. 2 nach Beschriebsberichtigung unter BV-Nr. 3 neu vorgetragen am 25.05.2007. [redacted]		

Fortsetzung auf Einlegebogen

Amtsgericht Rosenheim
Grundbuch von Halfing **Blatt** 2490 **Erste Abteilung** Einlegebogen 1

Lfd. Nr. der Eintragungen	Eigentümer	Lfd. Nr. der Grundstücke im Bestandsverzeichnis	Grundlage der Eintragung
1	2	3	4
1	[redacted], geb. [redacted]	1	Auflassungen vom 18.06. und 12.06.1998; eingetragen am 03.12.1998 [redacted]
2	[redacted], geb. am	3	Auflassung vom 15.12.2015; eingetragen am 18.04.2016. [redacted]

Anlage 8
Grundbuchauszug
A8.2

Amtsgericht Rosenheim
Grundbuch von Halfing **Blatt** 2490 **Erste Abteilung** Einlegebogen 1 R

Lfd. Nr. der Eintragungen	Eigentümer	Lfd. Nr. der Grundstücke im Bestandsverzeichnis	Grundlage der Eintragung
1	2	3	4

Fortsetzung auf Einlegebogen

Amtsgericht Rosenheim
Grundbuch von Halfing **Blatt** 2490 **Zweite Abteilung** Einlegebogen 1

Lfd. Nr. der Eintragungen	Lfd. Nr. der betroffenen Grundstücke im Bestandsverzeichnis	Lasten und Beschränkungen
1	1,2 ,3	Auflassungsvormerkung (Anspruch bedingt und befristet) für die [redacted]; gemäß Bewilligung vom 12.06.1998, Notar [redacted], Prien am Chiemsee, URNr. 840; Gleichrang mit Abt.II/2; Rang nach Abt.III/1; eingetragen am 03.12.1998 [redacted]
2	1,2 ,3	Vorkaufsrecht (befristet) für alle Verkaufsfälle für die [redacted], gemäß Bewilligung vom 12.06.1998, Notar [redacted], Prien am Chiemsee, URNr. 840; Gleichrang mit Abt.II/1; Rang nach Abt.III/1; eingetragen am 03.12.1998 [redacted]
3	3	Auflassungsvormerkung für [redacted], geb. am [redacted]; gemäß Bewilligung vom 15.12.2015 URNr. 1973/15 Notar [redacted], Ebersberg; Rang nach Abt. III/3; eingetragen am 25.01.2016. [redacted]
4	3	Auflassungsvormerkung (Anspruch bedingt und befristet) für [redacted]; gemäß Bewilligung vom 15.12.2015 URNr. 1973/15 Notar [redacted], Ebersberg; eingetragen am 18.04.2016. [redacted]
5	3	Die Zwangsversteigerung ist angeordnet (Amtsgericht Rosenheim, AZ: 801 K 24/23); eingetragen am 14.08.2023. [redacted]

Anlage 8
Grundbuchauszug
A8.3

Amtsgericht Rosenheim
Grundbuch von Halfing **Blatt** 2490 **Zweite Abteilung** Einlegebogen 1 R

Veränderungen		Löschungen	
Lfd. Nr. der Spalte 1		Lfd. Nr. der Spalte 1	
4	5	6	7
1,2	~~Abt. II/1,2 haben je Rang nach Abt. III/2; eingetragen am 23.05.2006.~~ [redacted]	1,3	Je gelöscht am 18.04.2016. [redacted]
2	Abt. II/2 hat Rang nach Abt. III/3; eingetragen am 25.01.2016. [redacted]		
2,4	Abt. II/2,4 haben Rang nach Abt. III/4; eingetragen am 02.03.2017. [redacted]		

Fortsetzung auf Einlegebogen

Anlage 9

Literaturverzeichnis

A 9

Literaturverzeichnis

Bürgerliches Gesetzbuch (BGB) *

Bayerische Bauordnung (BayBO)*

Baugesetzbuch (BauGB)*

Verordnung über Grundsätze für die Ermittlung der Verkehrswerte von Grundstücken (Immobilienwertermittlungsverordnung 2021 – ImmoWertV 2021)*

Verordnung über die bauliche Verordnung der Grundstücke (Baunutzungsverordnung – BauNVO)*

Jahresbericht des Gutachterausschusses für Grundstückswerte

Preisindizes für Bauwerke im Bundesgebiet

Abgekürzte Sterbetafeln 2020/2022 Deutschland

Verkehrswertermittlung von Grundstücken - Kleiber

Handbuch der Mietpreisbewertung für Wohn- und Gewerberaum - Dröge

Wohnflächenberechnung – Gerhard Heix

* Gesetze und Verordnungen in der zum Wertermittlungsstichtag jeweils gültigen Fassung